Manuel utilisateur du plugin « assistant complexe »
V0.1

Identifiant			Version	Date de création
			0.1	02/12/2024
Rédacteur	Gérôme PECHEUR			
Entité émettrice	DTSO			
Diffusion	☐ Interne	■ Ouverte	☐ Limitée	
Résumé	Installation et utilisation du plugin			
Approbateur		Date d'approbation	02/12/2024	

Lecteur(s)	

Version	Date	Modifié par	Historique des modifications
0.1		Gérôme PECHEUR	Création

Sommaire

1 PREREQUIS 2
2 RESUME 3
3 INSTALLATION 3
4 PRESENTATION 4
5 MODE DE SELECTION 5
5.1 Sélection unique 5
5.2 Sélection multiple 5
6 MODIFICATIONS D'UN COMPLEXE 5
7 EXTRA 6
7.1 Log 6
7.2 A propos de 6

1 Prérequis

Version de QGIS : 3.28 ou supérieur

Ce plugin fonctionne en parallèle du plugin « IGN Espace collaboratif » version 4.2.2

Ce plugin fonctionne uniquement avec des couches de la BDTopo, le nom de la couche route doit obligatoirement se nommer : « troncon_de_route » dans QGIS.

Si le package « openpyxl » n'est pas installé sur le poste le message d'erreur ci-dessous apparait lors d'une transaction.

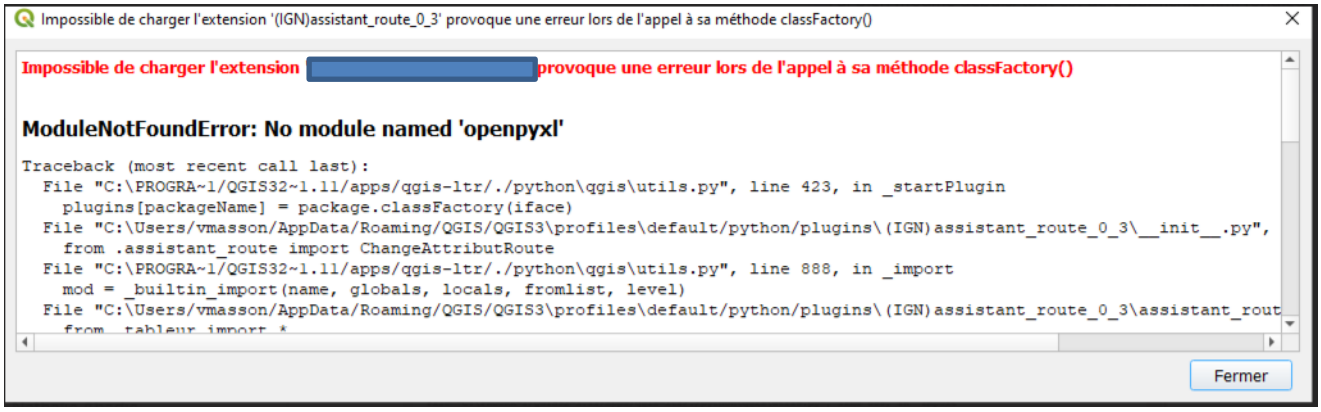

Remède : installation du package.

Ouvrir l'invite de commande, se placer dans le répertoire « bin » de l'installation de QGIS :

Exemple :

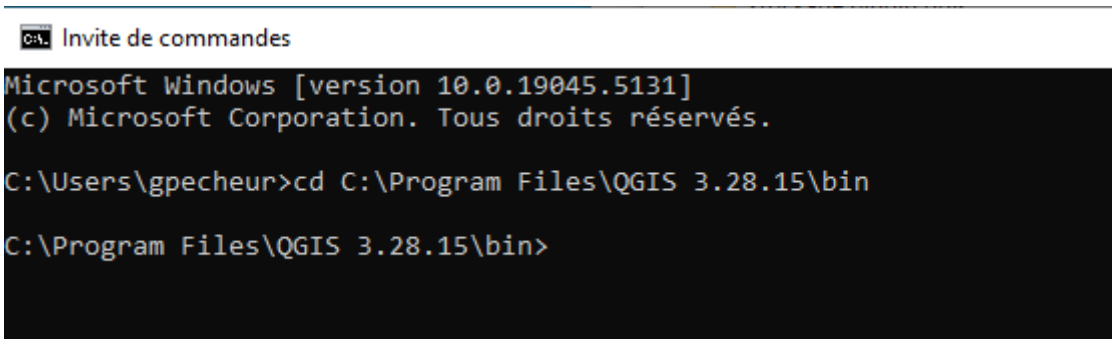

Puis taper la commande : python-qgis-ltr.bat -m pip install openpyxl

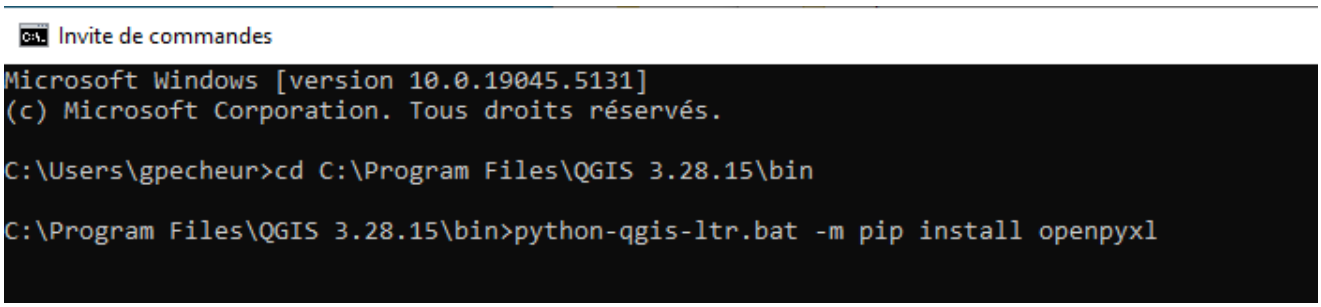

Le package s'installe, vous n'avez plus qu'à relancer QGIS.

2 Résumé

Ce plugin est une aide à l'ajout et au retrait des tronçons de route sur un complexe.

3 Installation

Ouvrir QGIS.

Allez dans Extensions/Installer/Gérer les extensions, cliquez sur Installer depuis un ZIP, sélectionner le fichier ZIP puis cliquez sur Installer le plugin.

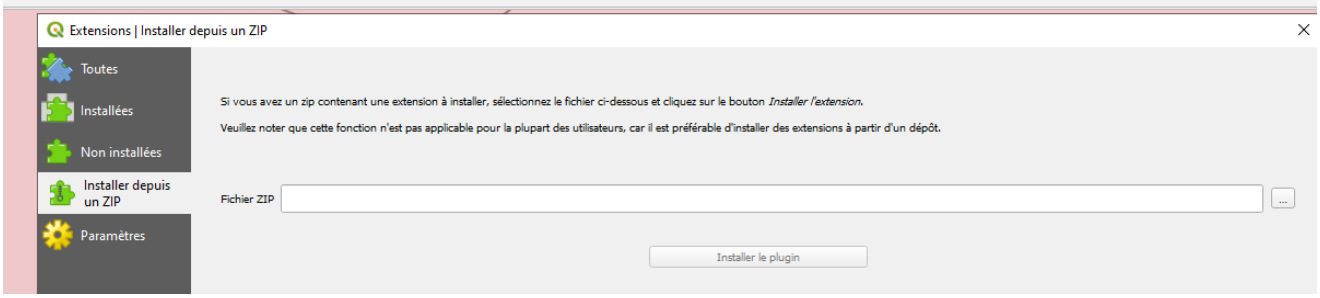

4 Présentation

Cette interface permet la modification d'un complexe en ajout ou en retrait.

Le bouton Ajouter permet d'ajouter la sélection au complexe sélectionné dans la liste.

Le bouton Retirer permet de retirer la sélection au complexe sélectionné dans la liste.

Le bouton Sélectionner les constituants permet de sélectionner tous les constituants (tronçons de route) du complexe choisi.

Le bouton à cliquer Fixer sert à fixer le complexe choisi afin de permettre la sélection de tronçons de roue pour ajout ou retrait du complexe.

Le bouton « ? » permet d'afficher le suivi des versions et permet également d'ouvrir la documentation du plugin
Le bouton « log » permet d'afficher le rapport des modifications

Le bouton permet d'annuler la dernière modification effective et uniquement la dernière.

Le bouton Chemin le plus court permet de sélectionner tous les tronçons compris entre 2 tronçons

5 Mode de sélection

L'interface permet de modifier la couleur de la sélection des tronçons dans QGIS, en fonction de la symbologie des tronçons il peut être judicieux d'en modifier la couleur

5.1 Sélection unique

- Sélection unique, on ne sélectionne qu'un seul tronçon avec l'outil de sélection de QGIS

5.2 Sélection multiple

- Sélection multiple avec l'outil de saisi. Dans QGIS on peut sélectionner manuellement un ensemble de tronçons

- Sélection multiple de tronçons contigües, on sélectionne 2, Ces 2 tronçons doivent être visible à l'écran et être connectés. Ensuite en clique sur [Chemin le plus court], le résultat est une sélection de tous les tronçons entre le premier et le deuxième sélectionné respectant l'algorithme du chemin le plus court. Un contrôle visuel est toutefois nécessaire afin de vérifier si les tronçons sont bien ceux désirés.

6 Modifications d'un complexe

- Lors de la sélection d'un tronçon ET un seul, l'interface affiche la liste des complexes associés.

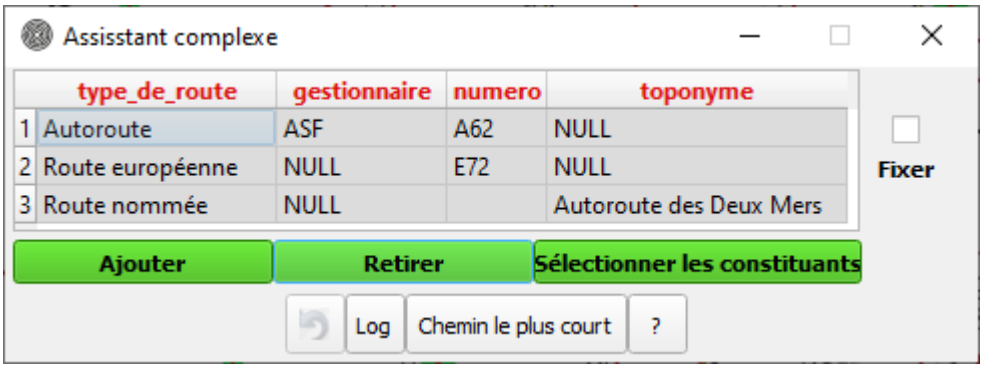

- On sélectionne le complexe à modifier. La case à cocher passe automatiquement à « cochée »

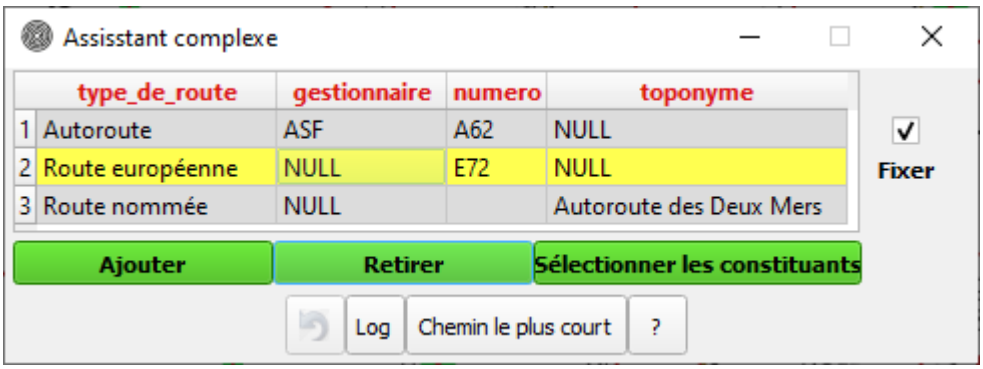

- Le complexe étant fixé on peut :
  - Sélectionner les constituants avec : Sélectionner les constituants
  - Ajouter un ou plusieurs tronçon(s) au complexe avec : Ajouter
  - Retirer un ou plusieurs tronçon(s) au complexe avec : Retirer

7 Extra

7.1 Log

Après chaque transaction, un fichier de log est généré au format xlsx.

Il est visualisable via : log

Ce fichier contient toutes les modifications effectuées. Les champs modifiés apparaissent en rouge.

A1 | Date

	A	B	C	D	E
1	Date	N° de transaction	CLEABS	Avant: liens_vers_route_nommee	Apres: liens_vers_route_nommee
2	02 December 2024 08:05	En cours de dévo	TRONROUT0000000092977774	NULL	NULL/ROUTNOMM0000000092996435
3	02 December 2024 08:04	En cours de dévo	TRONROUT0000000092977770	NULL	NULL/ROUTNOMM0000000092996435

7.2 A propos de

Accessible via ?.

Cette boite permet de suivre l'évolution des différentes versions ainsi que d'afficher cette documentation.